UNIDAD DE VIGILANCIA DE LA SALUD
REGIÓN METROPOLITANA DEL DISTRITO CENTRAL
BOLETIN ARBOVIROSIS SE 11
ELABORADOR POR MSC. DRA GLENDA CERRATO

Total, de casos sospechoso de Arbovirosis, hasta la Semana epidemiológica (SE) 11 RSM DC 2026

Gráfico 1 Casos de Dengue 2022-2025 (hasta la SE 11) 2026 en el Distrito Central RSM DC

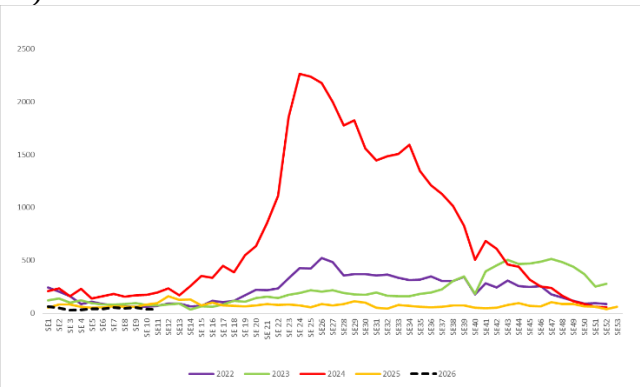

Fuente: Datos Área Gestión de la Información RSM 2026

Situación epidemiológica Dengue Región Sanitaria #19, Honduras SE 11 / año 2026.

En la SE 11 del año 2026, en el Distrito Central se registra un acumulado de 481 casos sospechosos de dengue, de los cuales en la SE 11 se reportan 37 casos (100%) de dengue sin signos de alarma, así mismo cero casos (0%) de dengue con signos de alarma y 0 casos (0%) de dengue grave, un total de 37 casos.

Tabla No.1 Tasa de Incidencia SE 1-11 RSMDC, Año2025&2026

Tasa de la Región 2025	55 casos
Tasa de la Región 2026	35 casos
Tasa por cada 100mil habitantes	

En el año 2025, la región registró una tasa de incidencia de 55 casos por cada 100,000 habitantes, mientras que en 2026 esta se redujo a 35 casos por cada 100,000 habitantes, lo que representa una disminución de 20 casos y una reducción aproximada del 36%.

Este comportamiento evidencia una disminución en la transmisión; no obstante, el riesgo persiste, por lo que resulta necesario fortalecer las estrategias de vigilancia epidemiológica, control vectorial y detección oportuna de casos, a fin de prevenir un posible repunte o la expansión del riesgo en períodos posteriores.

UNIDAD DE VIGILANCIA DE LA SALUD
REGIÓN METROPOLITANA DEL DISTRITO CENTRAL
BOLETIN ARBOVIROSIS SE 11
ELABORADOR POR MSC. DRA GLENDA CERRATO

Tabla 2 Indicadores vigilancia SE 11 RSM DC 2026

Indicadores	Acumulado SE 1-11	SE 11
Dengue No Grave	**480**	**37**
Dengue Grave	**1**	**0**
Zika	**0**	**0**
Chik:	**0**	**0**
Muertes	**0**	**0**
Tasa Dengue No Grave por c/100,000	**35**	**3**
Tasa Dengue Grave por c/ 100,000 hab.	**0.07**	**0**
Tasa de Chikunguña por c/ 100,000 hab.	**0**	**0**
Tasa de Zika por c/ 100,000 hab.	**0**	**0**
Tasa de Mortalidad	**0**	**0**

Tabla No. 3 Tasa de Mortalidad SE 11 RSMDC, Año 2025&2026

Año	Casos	Tasa c/100,000 hab
2025	Casos (1)	0.07
2026	Casos (0)	0

Fuente: Base arbovirosis Área Gestión e la Información RSM 2026

En 2025 se registró 1 caso, con una tasa de 0.07 por cada 100,000 habitantes, mientras que en 2026 no se notificaron casos, manteniéndose la tasa en 0. Este comportamiento indica ausencia de transmisión en 2026 y sugiere efectividad de las acciones de vigilancia y control, aunque es necesario mantenerlas para prevenir reintroducción del evento.

Tabla 4 Casos Dengue por Establecimiento de Salud, Semana Epidemiológica 7-10 RSM DC 2026

ES POR PROCENDENCIA. DENGUE	SE 8	9	10	11	Total general
SAN_MIGUEL	5	5	5	4	19
ALONSO_SUAZO	4	4	2	3	13
VILLA_ADELA	2	2	1	5	10
MANCHEN_EL	1	3	2	4	10
CRUCITAS_LAS	1	2	5		8
VILLA_NUEVA	3	2	2	1	8
SAN_BENITO	3	1	1	2	7
TIZATILLO	1	2	3		6
ALEMANIA_LA	2	1		3	6
NUEVA_SUYAPA	2	3		1	6

**colonias con mayor número de casos

Fuente: Datos Área Gestión de la Información RSM 2026

Mapa 1 Situación georreferencial casos dengue según establecimientos de salud SE 10-11 RSM DC 2026.

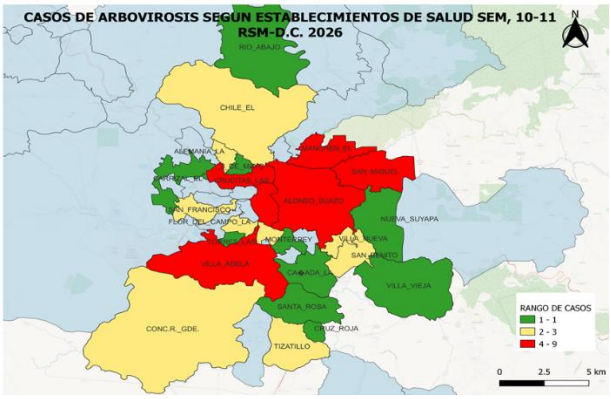

Fuente: Base arbovirosis, UVS RSM 2026

Durante la semana epidemiológica (SE) 11 de 2025 se notificaron 97 casos sospechosos de dengue, mientras que en la SE 11 de 2026 se registraron 37 casos sospechosos, evidenciando una disminución en la notificación. Para el año 2026, el comportamiento epidemiológico, de acuerdo con el corredor endémico, se mantiene dentro de la ***zona de éxito***, sin

UNIDAD DE VIGILANCIA DE LA SALUD
REGIÓN METROPOLITANA DEL DISTRITO CENTRAL
BOLETIN ARBOVIROSIS SE 11
ELABORADOR POR MSC. DRA GLENDA CERRATO

superar el umbral de alerta, lo que sugiere una transmisión controlada en el período analizado.

Mapa 2 Situación georreferencial casos dengue según colonias SE 10-11 RSM DC 2026

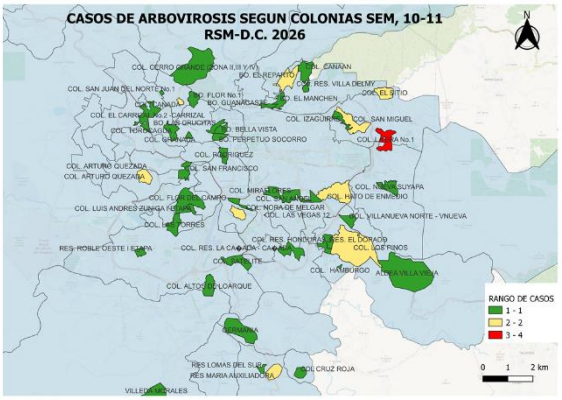

Fuente: Base arbovirosis Área Gestión e la Información RSM 2026

De las 1,114 colonias y barrios georreferenciados del Distrito Central, registraron casos de arbovirosis. Durante la semana epidemiológica 11, las colonias con mayor número de casos de dengue fueron: *Col. los Pinos, Col., Villa Nueva norte, Col. Era. No. 1 col Nueva Suyapa, Col. Kennedy, Col. San Miguel*

Asimismo, dentro de las áreas con mayor positividad en ovitrampas durante la SE 11 se identifican: ***UAPS Nueva Capital86%, CIS Villa Nueva 50%, Carrizal 46% Edén 44%, Crucitas 46%*** que evidencia la persistencia de criaderos y una alta densidad vectorial que requiere reforzar las intervenciones de control en estas zonas prioritarias.

Gráfico 3 Casos Dengue según clasificación diagnostica, SE 8-11 RSM DC 2026.

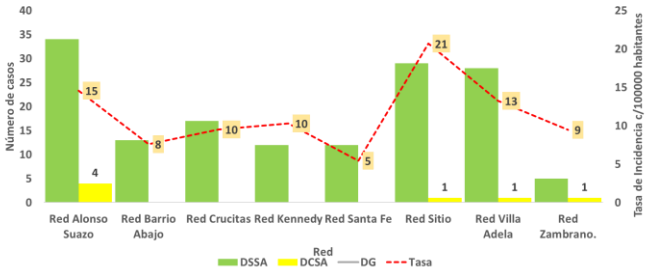

La Red El Sitio concentran las mayores tasas de incidencia, con 21 casos por cada 100,000 habitantes, seguidas por la Red el alonso Suazo con 15 casos por cada 100,000 habitantes, lo que evidencia una mayor carga de transmisión en estas áreas.

En contraste, las redes Santa Fe, Crucitas y Barrio Abajo presentan un menor número de casos y tasas más bajas; no obstante, requieren vigilancia epidemiológica sostenida para prevenir posibles rebrotes.

Tabla 4 Casos de dengue según colonias SE 8- 11 RSM DC 2026

COLONIAS	SE				
DENGUE	8	9	10	11	Total general
COL. LOS PINOS	3	1	1	1	6
COL. VILLANUEVA NORTE - VNUEVA	3	2	1		6
COL. LA ERA No.1	2		3	1	6
COL. NUEVA SUYAPA	2	2		1	5
COL. KENNEDY	3	2			5
COL. SAN MIGUEL		2		2	4
RIO HONDO		4			4
COL. RES. FRANCISCO MORAZAN	2	1			3
ALDEA LA TRAVESIA	1	2			3

UNIDAD DE VIGILANCIA DE LA SALUD
REGIÓN METROPOLITANA DEL DISTRITO CENTRAL
BOLETIN ARBOVIROSIS SE 11
ELABORADOR POR MSC. DRA GLENDA CERRATO

Gráfico 4 Indicadores por Grupo etario SE (11) RSM DC 2026

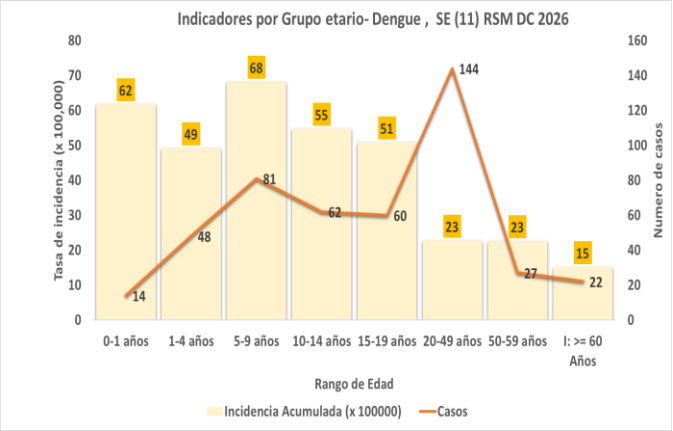

Las tasas de incidencia más elevadas se observan en los grupos de 5–9 años (68 por 100,000 habitantes), seguidos de la población de 0-1 años (62 por 100,000 habitantes),1–4 años, (49 por 100,000 habitantes), 15–19 años (51 por 100,000 habitantes) lo que evidencia mayor riesgo epidemiológico en población pediátrica y adolescente. En términos de casos, el grupo de 20–49 años concentra el mayor número de casos (144 casos); sin embargo, su incidencia relativa es menor en comparación con otros grupos etarios, atribuible a su mayor tamaño poblacional.

La población de 50 años y más presenta baja incidencia (23 por 100,000 habitantes) y un número reducido de casos; no obstante, debido a su mayor vulnerabilidad clínica, requiere detección temprana y seguimiento oportuno.

Mapa 3 mapa de dengue con signos de alarma según colonias SE 10-11 RSM DC 2026.

Durante las semanas epidemiológicas 1 a 11 del año 2026 se han notificado 35 casos de dengue con signos de alarma en el área de la Región Sanitaria Metropolitana del Distrito Central.

Los casos se distribuyen en diferentes colonias del Distrito Central, evidenciando una dispersión geográfica del evento. Esta situación indica circulación activa del virus del dengue en el territorio. Ante ello, es necesario fortalecer la vigilancia epidemiológica y las acciones de control vectorial en las zonas afectadas. Asimismo, se recomienda intensificar las actividades de prevención y eliminación de criaderos para reducir el riesgo de transmisión.

UNIDAD DE VIGILANCIA DE LA SALUD
REGIÓN METROPOLITANA DEL DISTRITO CENTRAL
BOLETIN ARBOVIROSIS SE 11
ELABORADOR POR MSC. DRA GLENDA CERRATO

Gráfico 4 Corredor endémica dengue (dengue sin signos de alarma, con signos de alarma y dengue grave SE 11

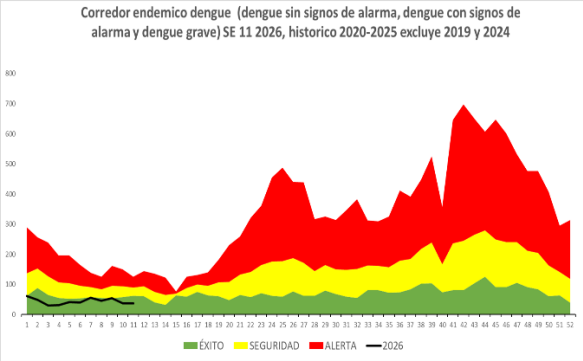

Tabla 5 Casos de dengue con signos de alarma según colonias SE 8-11 RSM DC 2026

DENGUE CON SIGNOS DE ALARMA.	SE				
DENGUE	8	9	10	11	Total general
COL. LOS PINOS	1				1
COL. NUEVA SUYAPA		1			1
COL. LUIS ANDRES ZUNIGA I ETAPA			1		1
BO. MORAZAN		1			1
SAN FRANCISCO			1		1
COL. KENNEDY		1			1
COL. LA ERA No.1			1		1

SISTEMA DE INFORMACIÓN ARBOVIROSIS

Tabla 8 Casos de dengue según notificante y diagnóstico de 1 y 2do nivel atención. SE 11 año 2026 RSM DC

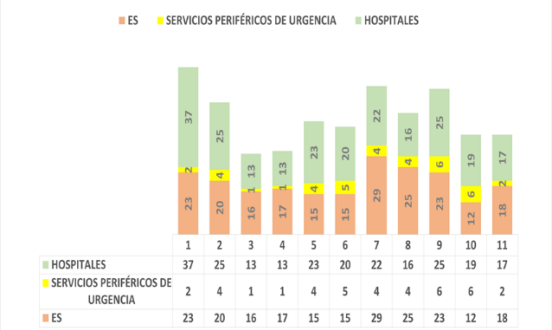

	1	2	3	4	5	6	7	8	9	10	11
HOSPITALES	37	25	13	13	23	20	22	16	25	19	17
SERVICIOS PERIFÉRICOS DE URGENCIA	2	4	1	1	4	5	4	4	6	6	2
ES	23	20	16	17	15	15	29	25	23	12	18

Fuente: Base arbovirosis, UVS RSM 2026

*****Notificantes con mayor notificación.***

De la red de notificación del Distrito central, en la SE 11 los CIS/UAPS atendieron 49% (18 casos), los hospitales con un 46% (17 casos), y en menor proporción los servicios periféricos de urgencia con 5% (2 casos) esta semana.

Gráfico 4: Casos de dengue en base de dengue de la UVS, Oficial del telegrama de y en SNVS según SE 1-11, RSM DC

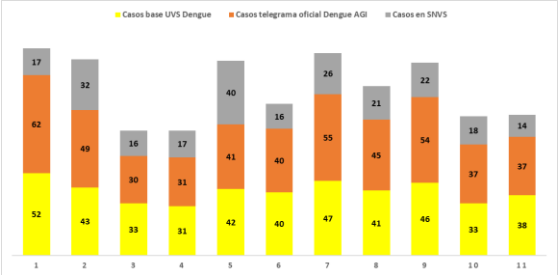

Tabla 9 Casos de dengue según sistema de notificación SE 1-11 RSM DC 2026.

		1	2	3	4	5	6	7	8	9	10	11
2026	Casos base UVS Dengue	52	43	33	31	42	40	47	41	46	33	38
	Casos telegrama oficial Dengue AGI	62	49	30	31	41	40	55	45	54	37	37
	Casos en SNVS	17	32	16	17	40	16	26	21	22	18	14

En el acumulado de las SE 1–11 de 2026, el telegrama oficial registró 485 casos de dengue, mientras que la base UVS notificó 446 casos y el SNVS 239 casos, evidenciando desfases en la notificación y consolidación de datos y la necesidad de fortalecer la unificación de sistemas de información.

ACTIVIDADES DE CONTROL VECTORIAL

- Se está ejecutando un plan de intervención basado en la Estrategia de Gestión Integrada para la prevención de enfermedades transmitidas por vectores, con énfasis en dengue. Las acciones incluyen fumigación en sitios de riesgo con máquinas LECO y térmicas, de acuerdo con el análisis epidemiológico de la UVS-RSM, además de la difusión de información sobre la situación del dengue en el país y las medidas de prevención y control.
- Presentación de la situación epidemiológica del dengue y programación semanal de colonias con mayor incidencia, priorizadas según riesgo, a cargo de los técnicos de la Unidad de Vigilancia, con la participación de COPECO, CODEM, OPS/OMS, AMDC, Secretaría de Educación y Cuerpo de Bomberos, para la ejecución de actividades de control vectorial.

- Realización de salas situacionales de dengue con el equipo regional para la toma oportuna de decisiones en el Distrito Central.

- Reunión técnica regional semanal para análisis epidemiológico y entomológico para focalizar acciones de control vectorial.
- Programar visitas técnicas regional para mejorar el sistema de Información en el SNVS, AR-Base de datos de arbovirosis
- Se programaron en la SE 11 un total de viviendas programadas: 8,999 Inspeccionadas: 5,068 cerradas: 1,135, renuentes: 562, viviendas, deshabitadas: 88, índice por vivienda no inspeccionada 7%, tratadas con BTI: 4,744 sitios de alto riesgos inspeccionados: 802 positivo: 75 Tratados con BTI: 279 nebulizados: 414
- Depósitos: inspeccionados: 935, positivos: 56 Tratado con BTI; 604 gramos, eliminados 65
- Gasto total: BTI: **41,789** aquareslin, **21,100**
- Actualización cartográfica de los CIS/UAPS en Coordinación con MSF (médicos sin fronteras) para georreferenciar las colonias del Distrito Central de la zona urbana
- Análisis de Hot spot para intervención de los sitios de riesgos.
- Mejorar la vigilancia de entomológica mediante análisis de Hot Spot (CIS Villa Nueva/ CIS los Pinos) con apoyo de programa de vectores, OPS/OMS
- Realización de actividades de control vectorial (control larvario y control adultecita) en los albergues.

UNIDAD DE ENTOMOLOGIA

Gráfico 7 comparativos índices de positividad EN Ovitrampas años 2025-2026 SE 11 RSM DC

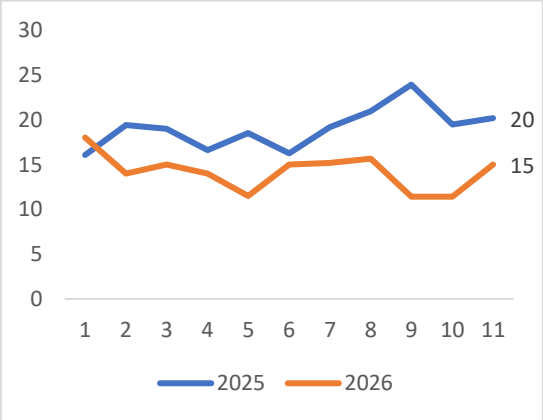

- En la gráfica se observa el comportamiento de los índices de positividad en la semana No.11 del año 2025 con 20% y en el año 2026 con 15%.
- 33 ovitrampas No inspeccionadas.
- 6% es el porcentaje de perdida de información ya que hay establecimientos de salud que no han habilitado el total de ovitrampas instaladas, extraviadas o cerradas.
- 4% aumentó la oviposturas en comparación a la semana anterior.
- 1% aumentó el índice de positividad en comparación a la semana anterior.
- 41 establecimientos realizaron la vigilancia entomológica.
- Se programa en mesa municipal las colonias ***CIS villa nueva: Villa Nueva Sector 5 y CIS Los pinos: Colonia los pinos.***
-
- **Gráfico 8.-** oviposturas en ovitrampas SE 11 2025-2026 RSM DC

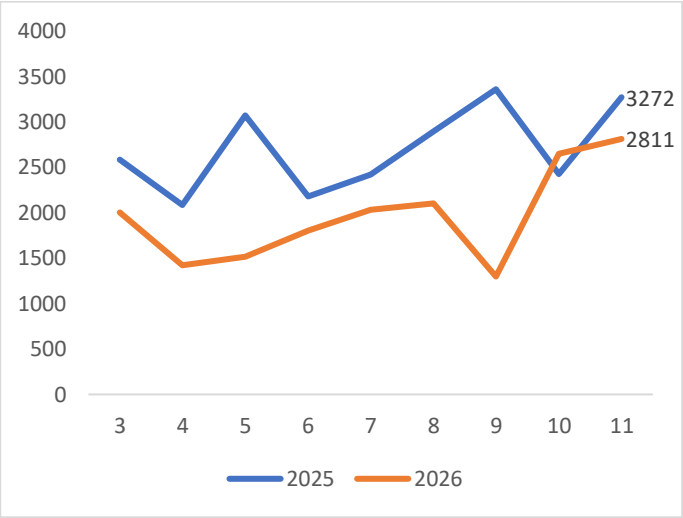

Tabla 10 Informe Semanal de Ovitrampas Por Red
SE 11 RSM DC 2026.

N°	ESTABLECIMIENTO DE SALUD	SEMANA # 11				
		INST.	INSP.	POSIT	%	No. HUEVOS
	1- RED LAS CRUCITAS					
1	LAS CRUCITAS	12	12	5	42	295
2	3 DE MAYO	10	10	2	20	62
3	DIVANNA	10	9	1	11	50
4	ALEMANIA	10	10	2	20	74
5	LA CUESTA	9	9	1	11	18
6	SAN FRANCISCO DE SOROGUARA	S	S	S	0	0
	2- RED SANTA FE					
7	EL CARRIZAL	15	13	6	46	162
8	NUEVA CAPITAL	16	14	12	86	475
9	LA SAN FRANCISCO	15	14	1	7	6
10	C. A. O.	14	14	0	0	0
11	21 DE FEBRERO	19	19	1	5	32
12	EL EDEN	9	9	4	44	24
	3- RED VILLA ADELA					
13	VILLA ADELA	12	12	1	8	14
14	CRUZ ROJA	4	4	1	25	122
15	ALDEA SANTA ROSA	10	9	4	44	64
16	YAGUACIRE	7	7	2	29	**75**
17	CONCEP. DE RIO GRANDE	12	12	0	0	0
18	FLOR DEL CAMPO	11	11	4	36	164
19	LAS TORRES	20	18	7	39	277
20	NUEVA ESPERANZA	14	14	6	43	138
21	TIZATILLO	S	S	S	S	0
	MATEO	8	8	0	0	0
	4- RED EL SITIO					
22	SAN MIGUEL	9	9	0	0	0
23	EL MANCHEN	42	42	2	5	62
	5- RED BARRIO ABAJO					
24	EL CHILE	15	14	3	21	70
25	EL BOSQUE	11	10	0	0	0
26	CARPINTERO	4	S	S	0	0
27	BRISAS DE PICACHO	5	5	2	40	30
28	I.H.S.S. BARRIO ABAJO	S	S	S	0	0
	6- RED KENNEDY					
29	EL PEDREGAL	16	11	0	0	0
30	AEROPUERTO TONCONTIN	S	S	S	S	0
31	LA PEÑA (S.H.)	8	8	0	0	0
32	OSCAR A. FLORES	6	4	0	0	0
33	LA CAÑADA	11	11	0	0	0
34	LA JOYA	13	13	4	31	167
35	MONTERREY	14	14	0	0	0
	7- RED ALONSO SUAZO					
36	ALONSO SUAZO	59	56	5	9	139
37	LOS PINOS	18	18	2	11	8
38	ALDEA VILLA VIEJA	8	8	3	38	50
39	VILLA NUEVA	16	16	8	50	123
40	NUEVA SUYAPA	11	11	2	18	44
	8- RED ZAMBRANO					
41	ZAMBRANO	9	9	0	0	0
42	TAMARA	9	9	3	33	47
43	SAN MIGUEL ARCANGEL	6	**6**	**0**	0	0
44	CIUDAD ESPAÑA	10	10	2	20	19
45	VILLA EL PORVENIR	S	S	S	0	**0**
46	UAPS RIO FRIO	8	S	S	S	**0**
	TOTAL	**545**	**512**	**96**	**15**	**2811**

Programación Mesa Municipal Intersectorial

NO	COLONIAS/BARRIOS	VIVIENDAS ATENDER	ACTIVIDAD	RESPONSABLES	FECHA	PUNTO DE REUNION
1	CIS Villanueva Col. Villa Nueva Sector 5	250	Fumigacion/aplicación BTI/ Fumigación MAQUINA LECO	RSM DC /CIS	30-31 de marzo	Entrada al sector N.5
2	CIS Los Pinos Sector A	250	Fumigacion/aplicación BTI/ Fumigación MAQUINA LECO	RSM DC /CIS	30- 31 de marzo	CIS Los Pinos

PROGRAMACIÓN MAQUINAS LECO

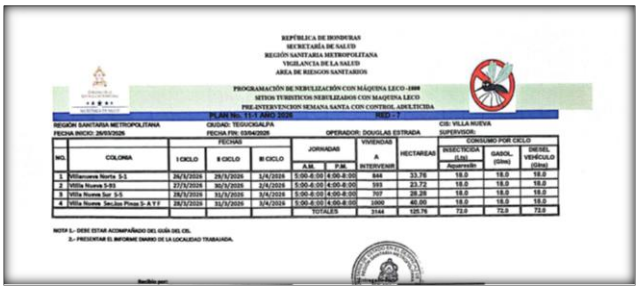
REPÚBLICA DE HONDURAS
SECRETARÍA DE SALUD
REGIÓN SANITARIA METROPOLITANA
VIGILANCIA DE LA SALUD
AREA DE RIESGOS SANITARIOS

PROGRAMACIÓN DE NEBULIZACIÓN CON MÁQUINA LECO-4000
SITIOS TURISTICOS NEBULIZADOS CON MAQUINA LECO
PRE-INTERVENCION SEMANA SANTA CON CONTROL ADULTO/CIDA

PLAN No. 11-1 AÑO 2026 RED : 7

REGION SANITARIA METROPOLITANA CIUDAD: TEGUCIGALPA CIS: VILLA NUEVA
FECHA INICIO: 26/03/2026 FECHA FIN: 03/04/2026 OPERADOR: DOUGLAS ESTRADA SUPERVISOR:

NO.	COLONIA	FECHAS			JORNADAS		VIVIENDAS A INTERVENIR	HECTAREAS	CONSUMO POR CICLO		
		I CICLO	II CICLO	III CICLO	A.M.	P.M.			INSECTICIDA (Lbs) Asperminb	GASOL. (Gln)	DIESEL VEHÍCULO (Gln)
1	Villanueva Norte S-1	26/3/2026	29/3/2026	1/4/2026	5:00-6:00	4:00-6:00	844	33.76	18.0	18.0	18.0
2	Villa Nueva S-03	27/3/2026	30/3/2026	2/4/2026	5:00-6:00	4:00-6:00	303	23.72	18.0	18.0	18.0
3	Villa Nueva Sur 3-5	28/3/2026	31/3/2026	3/4/2026	5:00-6:00	4:00-6:00	707	28.28	18.0	18.0	18.0
4	Villa Nueva Sector Pinos 3- A Y F	29/3/2026	01/3/2026	5/4/2026	5:00-6:00	4:00-6:00	1000	40.00	18.0	18.0	18.0
					TOTALES		3144	125.76	72.0	72.0	72.0

NOTA 1.- DEBE ESTAR ACOMPAÑADO DEL GUÍA DEL CIS.
2.- PRESENTAR EL INFORME DIARIO DE LA LOCALIDAD TRABAJADA.