Total, de casos sospechoso de Arbovirosis, hasta la Semana epidemiológica (SE) 9 RSM DC 2026

Gráfico 1 Casos de Dengue 2022-2025 (hasta la SE 9) 2026 en el Distrito Central RSM DC

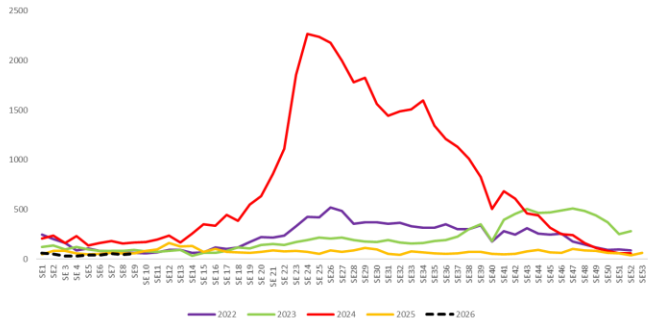

Fuente: Datos Área Gestión de la Información RSM 2026

Situación epidemiológica Dengue Región Sanitaria #19, Honduras SE 9 / año 2026.

En la SE 9 del año 2026, en el Distrito Central se registra un acumulado de 407 casos sospechosos de dengue, de los cuales en la SE 9 se reportan 51(94%) casos de dengue sin signos de alarma, así mismo 3 casos (6%) de dengue con signos de alarma y 0 caso (0%) de dengue grave, un total de 54 casos.

Tabla No.1 Tasa de Incidencia SE 1-9 RSMDC, Año2025&2026

Tasa de la Región 2025	41 casos
Tasa de la Región 2026	30 casos
Tasa por cada 100mil habitantes	

En el año 2025, la región registró una tasa de incidencia de 41 casos por cada 100,000 habitantes, mientras que en 2026 esta se redujo a 30 casos por cada 100,000 habitantes, lo que representa una disminución de 11 casos y una reducción aproximada del 27 %.

Este comportamiento evidencia una disminución en la transmisión; no obstante, el riesgo persiste, por lo que resulta necesario fortalecer las estrategias de vigilancia epidemiológica, control vectorial y detección oportuna de casos, a fin de prevenir un posible repunte o la expansión del riesgo en períodos posteriores.

Tabla 2 Indicadores vigilancia SE 9 RSM DC 2026

Indicadores	Acumulado SE 1-9	SE 9
Dengue No Grave	**406**	**54**
Dengue Grave	**1**	**0**
Zika	**0**	**0**
Chik:	**0**	**0**
Muertes	**0**	**0**
Tasa Dengue No Grave por c/100,000	**29**	**4**
Tasa Dengue Grave por c/ 100,000 hab.	**0.07**	**0**
Tasa de Chikunguña por c/ 100,000 hab.	**0**	**0**
Tasa de Zika por c/ 100,000 hab.	**0**	**0**
Tasa de Mortalidad	**0**	**0**

Tabla No. 3 Tasa de Mortalidad SE 9 RSMDC, Año 2025&2026

Año	Casos	Tasa c/100,000 hab
2025	Casos (1)	0.07
2026	Casos (0)	0

Fuente: Base arbovirosis Área Gestión e la Información RSM 2026

En 2025 se registró 1 caso, con una tasa de 0.07 por cada 100,000 habitantes, mientras que en 2026 no se notificaron casos, manteniéndose la tasa en 0. Este comportamiento indica ausencia de transmisión en 2026 y sugiere efectividad de las acciones de vigilancia y control, aunque es necesario mantenerlas para prevenir reintroducción del evento.

Tabla 4 Casos Dengue por Establecimiento de Salud, Semana Epidemiológica 5-9 RSM DC 2026

ES POR PROCENDENCIA. SE						
DENGUE	5	6	7	8	9	Total general
ALONSO_SUAZO	2	2	10	4	4	22
SAN_MIGUEL	5	2	5	5	5	22
VILLA_NUEVA	3	2	2	3	2	12
MANCHEN_EL	2	3	2	1	3	11
VILLA_ADELA	3		3	2	2	10
BOSQUE_EL	2	2	1	2	1	8
SAN_BENITO		1	2	3	1	7
ALEMANIA_LA	1	1	2	2	1	7
EDEN_EL	2	2		2	1	7
CRUCITAS_LAS	2	1	1	1	2	7

**colonias con mayor número de casos

Fuente: Datos Área Gestión de la Información RSM 2026

Mapa 1 Situación georreferencial casos dengue según establecimientos de salud SE 8-9 RSM DC 2026.

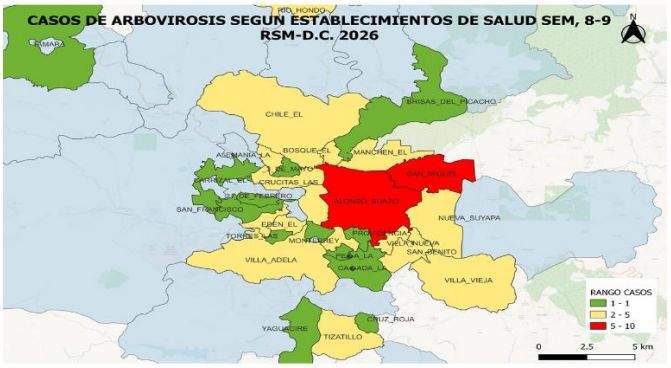

Fuente: Datos Área Gestión de la Información RSM 2026

Durante la semana epidemiológica (SE) 9 de 2025 se notificaron 61 casos sospechosos de dengue, mientras que en la SE 9 de 2026 se registraron 54 casos sospechosos, evidenciando una disminución en la notificación. Para el año 2026, el comportamiento epidemiológico, de acuerdo con el corredor endémico, se mantiene dentro de la ***zona de éxito***, sin superar el umbral de alerta, lo que sugiere una transmisión controlada en el período analizado.

Mapa 2 Situación georreferencial casos dengue según colonias SE 8-9 RSM DC 2026

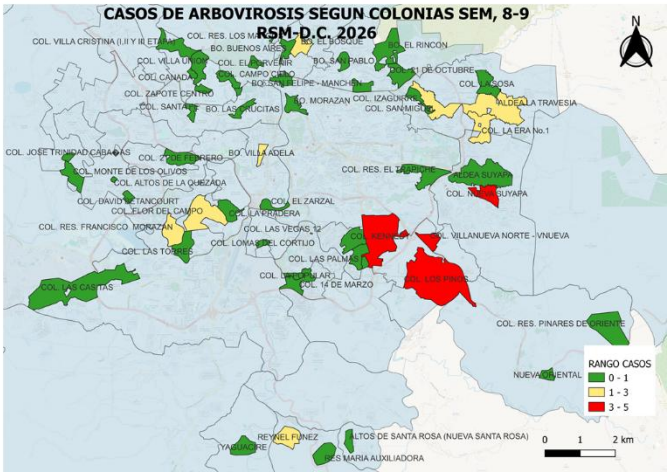

Fuente: Base arbovirosis Área Gestión e la Información RSM 2026

De las 1,114 colonias y barrios georreferenciados del Distrito Central, registraron casos de arbovirosis. Durante la semana epidemiológica 9, las colonias con mayor número de casos de dengue fueron: *Col. Villa Nueva norte, Col Kennedy, Col. los Pinos, Flor del campo y Nueva Suyapa.* Asimismo, dentro de las áreas con mayor positividad en ovitrampas durante la SE 9 se identifican: *CIS Crucitas 50%, CIS Villa Nueva 31%, CIS San Francisco 29%, UAPS Nueva Capital 27%, aldea Villa Vieja 25%* que evidencia la persistencia de criaderos y una alta densidad vectorial que requiere reforzar las intervenciones de control en estas zonas prioritarias.

Gráfico 3 Casos Dengue según clasificación diagnostica, SE 5-9 RSM DC 2026.

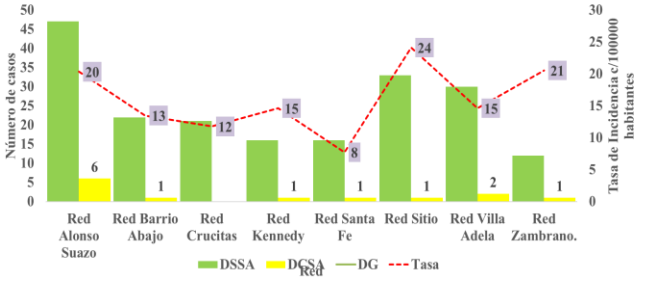

La Red El Sitio concentran las mayores tasas de incidencia, con 24 casos por cada 100,000 habitantes, seguidas por la Red el Sitio con 20 casos por cada 100,000 habitantes, lo que evidencia una mayor carga de transmisión en estas áreas.

En contraste, las redes Santa Fe, Crucitas y Barrio Abajo presentan un menor número de casos y tasas más bajas; no obstante, requieren vigilancia epidemiológica sostenida para prevenir posibles rebrotes.

Tabla 4 Casos de dengue según colonias SE 1- 9 RSM DC 2026

COLONIAS	SE					
DENGUE	5	6	7	8	9	Total general
COL. VILLANUEVA NORTE - VNUEVA	3	2	2	3	2	12
COL. KENNEDY			5	3	2	10
COL. LOS PINOS		1	1	3	1	6
COL. FLOR DEL CAMPO		2	2		2	6
COL. NUEVA SUYAPA			1	2	2	5
BO. EL BOSQUE	2	1		1	1	5
ALDEA LA TRAVESIA	1		1	1	2	5
COL. LAS TORRES	1	1	1		1	4
COL. HATO DE ENMEDIO	1		3			4
COL. SAN MIGUEL	1		1		2	4
RIO HONDO					4	4

Gráfico 4 Indicadores por Grupo etario SE (9) RSM DC 2026

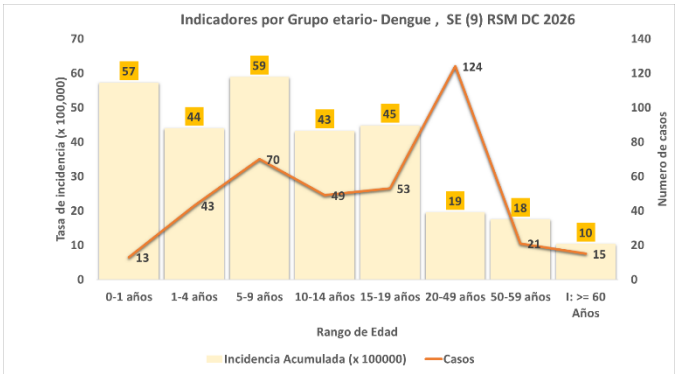

Mapa 3 mapa de dengue con signos de alarma según colonias SE 1-8 RSM DC 2026.

Las tasas de incidencia más elevadas se observan en los grupos de 5–9 años (59 por 100,000 habitantes), seguidos de la población de 0-1 años (57 por 100,000 habitantes),1–4 años, (44 por 100,000 habitantes), 15–19 años (35 por 100,000 habitantes) lo que evidencia mayor riesgo epidemiológico en población pediátrica y adolescente. En términos de casos, el grupo de 20–49 años concentra el mayor número de casos (113 casos); sin embargo, su incidencia relativa es menor en comparación con otros grupos etarios, atribuible a su mayor tamaño poblacional.

La población de 50 años y más presenta baja incidencia (15 por 100,000 habitantes) y un número reducido de casos; no obstante, debido a su mayor vulnerabilidad clínica, requiere detección temprana y seguimiento oportuno.

Tabla 5 Casos de dengue con signos de alarma según colonias SE 1-9 RSM DC 2026

DENGUE CON SIGNOS DE ALARMA.	SE					
DENGUE	5	6	7	8	9	Total general
COL. LAS BRISAS	1					1
COL. VILLANUEVA NORTE - VNUEVA			1			1
COL. MODESTO RODAS ALVARADO No.2		1				1
BO. MORAZAN				1		1
ZAMBRANO		1				1
CERRO JUAN A. LAINEZ		1				1
COL. LOS PINOS				1		1
COL. ALTOS DE SAN FRANCISCO	1					1
COL. NUEVA SUYAPA				1		1
COL. EL PORVENIR	1					1
LA SABANA	1					1
COL. KENNEDY				1		1
COL. LA PEÑA		1				1

Durante las semanas epidemiológicas 1 a 9 del año 2026 se han notificado 32 casos de dengue con signos de alarma en el área de la Región Sanitaria Metropolitana del Distrito Central.

Los casos se distribuyen en diferentes colonias del Distrito Central, evidenciando una dispersión geográfica del evento. Esta situación indica circulación activa del virus del dengue en el territorio. Ante ello, es necesario fortalecer la vigilancia epidemiológica y las acciones de control vectorial en las zonas afectadas. Asimismo, se recomienda intensificar las actividades de prevención y eliminación de criaderos para reducir el riesgo de transmisión.

Gráfico 4 Corredor endémica dengue (dengue sin signos de alarma, con signos de alarma y dengue grave SE 9

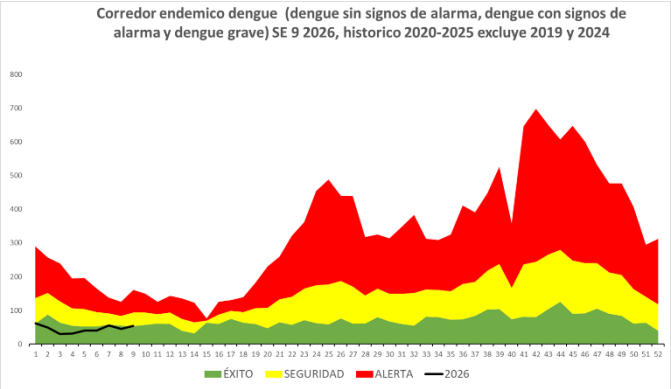

Tabla 8 Casos de dengue según notificante y diagnóstico de 1 y 2do nivel atención. SE 9 año 2026 RSM DC

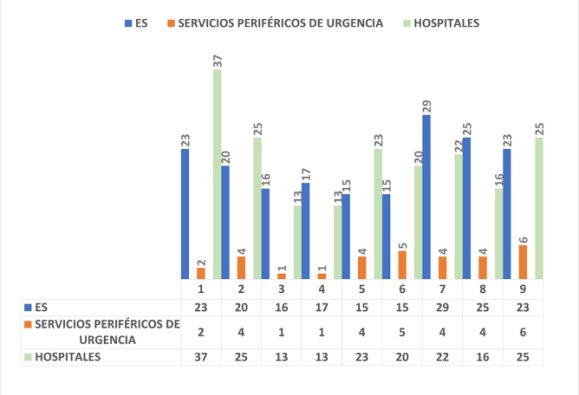

	1	2	3	4	5	6	7	8	9
ES	23	20	16	17	15	15	29	25	23
SERVICIOS PERIFÉRICOS DE URGENCIA	2	4	1	1	4	5	4	4	6
HOSPITALES	37	25	13	13	23	20	22	16	25

Fuente: Base arbovirosis, UVS RSM 2026

Colonias con mayor número de casos

De la red de notificación del Distrito central, en la SE 9 los CIS/UAPS atendieron 43% (23 casos), los hospitales con un 46% (25 casos), y en menor proporción los servicios periféricos de urgencia con 11% (6 casos) esta semana.

SISTEMA DE INFORMACIÓN ARBOVIROSIS

Gráfico 4: Casos de dengue en base de dengue de la UVS, Oficial del telegrama de y en SNVS según SE 1-9, RSM DC 2026

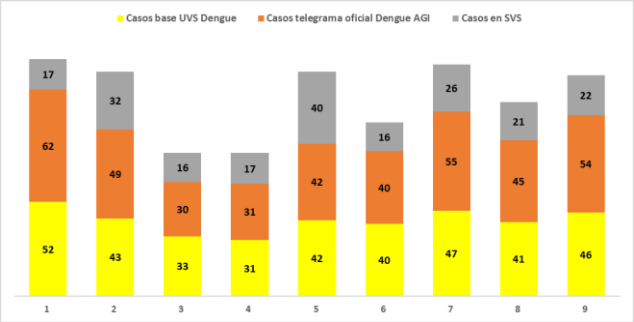

Tabla 9 Casos de dengue según sistema de notificación SE 1-9 RSM DC 2026.

		1	2	3	4	5	6	7	8	9
2026	Casos base UVS Dengue	52	43	33	31	42	40	47	41	46
	Casos telegrama oficial Dengue AGI	62	49	30	31	42	40	55	45	54
	Casos en SVS	17	32	16	17	40	16	26	21	22

En el acumulado de las SE 1–9 de 2026, el telegrama oficial registró 407 casos de dengue, mientras que la base UVS notificó 375 casos y el SNVS 207 casos, evidenciando desfases en la notificación y consolidación, evidenciando la necesidad de fortalecer la unificación de sistemas de información.

ACTIVIDADES DE CONTROL VECTORIAL

- Se está ejecutando un plan de intervención basado en la Estrategia de Gestión Integrada para la prevención de enfermedades transmitidas por vectores, con énfasis en dengue. Las acciones incluyen fumigación en sitios de riesgo con máquinas LECO y térmicas, de acuerdo con el análisis epidemiológico de la UVS-RSM, además de la difusión de información sobre la situación del dengue en el país y las medidas de prevención y control.
- Presentación de la situación epidemiológica del dengue y programación semanal de colonias con mayor incidencia, priorizadas según riesgo, a cargo de los técnicos de la Unidad de Vigilancia, con la participación de COPECO, CODEM, OPS/OMS, AMDC, Secretaría de Educación y Cuerpo de Bomberos, para la ejecución de actividades de control vectorial.
- Realización de salas situacionales de dengue con el equipo regional para la toma oportuna de decisiones en el Distrito Central.
- Reunión técnica regional semanal para análisis epidemiológico y entomológico para focalizar acciones de control vectorial.
- Programar visitas técnicas regional para mejorar el sistema de Información en el SNVS, AR-Base de datos de arbovirosis
- Se programaron en la SE 9 un total de viviendas programadas: 12,585 Inspeccionadas: 7,474, cerradas: 1,841, 512, renuentes: 700 viviendas, deshabitadas: 102, índice por vivienda no inspeccionada 21%
- %, tratadas con BTI: 32,614 Sitios de alto riesgos inspeccionados: 498, Positivo: 33, Tratados con BTI: 502, nebulizados: 292.
- Depósitos: **871,** inspeccionados: positivos: 53 Tratado con BTI; 502 gramos, eliminados 30
-

- Gasto total: BTI: **32,614, aquareslin 23,980**
- Actualización cartográfica de los CIS/UAPS en Coordinación con MSF (médicos sin fronteras) para georreferenciar las colonias del Distrito Central de la zona urbana
- Análisis de Hot spot para intervención de los sitios de riesgos.
- Mejorar la vigilancia de entomológica mediante análisis de Hot Spot (CIS Villa Nueva/ CIS los Pinos) con apoyo de programa de vectores, OPS/OMS
- Realización de actividades de control vectorial (control larvario y control adultecita) en los albergues.

UNIDAD DE ENTOMOLOGIA

- En la gráfica se observa el comportamiento de los índices de positividad en la semana No.7 del año 2025 con 19% y en el año 2026 con 15%.
- 27 ovitrampas no inspeccionadas
- 5% es el porcentaje de perdida de información ya que hay establecimientos de salud que no han habilitado el total de ovitrampas instaladas, extraviadas o cerradas.
- 4% aumento la oviposturas en comparación a la semana anterior.
- 1% aumentó el índice de positividad en comparación a la semana anterior.
- 41 establecimientos realizaron la vigilancia entomológica.
- Se programa en mesa municipal las colonias ***CIS villa nueva, CIS Alonso Suazo, CIS Nueva Suyapa***

Gráfico 8.- oviposturas en ovitrampas SE 9 2025-2026 RSM DC

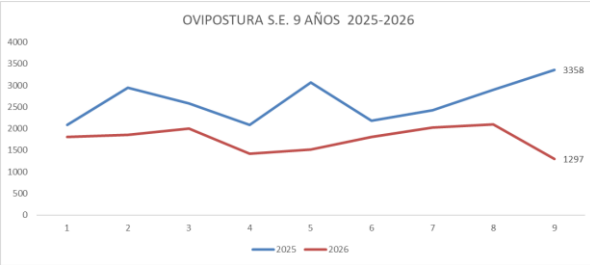

Tabla 10 Informe Semanal de Ovitrampas Por Red
SE 9 RSM DC 2026.

N°	ESTABLECIMIENTO DE SALUD	SEMANA # 09				
		INST.	INSP.	POSIT	%	No. HUEVOS
	1- RED LAS CRUCITAS					
1	LAS CRUCITAS	12	12	6	50	192
2	3 DE MAYO	10	10	0	0	0
3	DIVANNA	10	10	1	10	9
4	ALEMANIA	10	10	0	0	0
5	LA CUESTA	9	9	0	0	0
6	SAN FRANCISCO DE SOROGUARA	S	S	S	0	0
	2- RED SANTA FE					
7	EL CARRIZAL	15	15	0	0	0
8	NUEVA CAPITAL	16	15	4	27	264
9	LA SAN FRANCISCO	15	14	4	29	30
10	C. A. O.	14	14	2	14	7
11	21 DE FEBRERO	19	19	0	0	0
12	EL EDEN	9	9	1	11	21
	3- RED VILLA ADELA					
13	VILLA ADELA	12	12	2	17	43
14	CRUZ ROJA	4	4	1	25	65
15	ALDEA SANTA ROSA	10	9	1	11	28
16	YAGUACIRE	7	7	1	14	4
17	CONCEP. DE RIO GRANDE	12	12	0	0	0
18	FLOR DEL CAMPO	11	10	2	20	43
19	LAS TORRES	20	20	1	5	28
20	NUEVA ESPERANZA	14	14	1	7	12
21	TIZATILLO	S	S	S	0	0
	MATEO	8	8	1	13	3
	4- RED EL SITIO					
22	SAN MIGUEL	9	8	0	0	0
23	EL MANCHEN	42	42	1	2	47
	5- RED BARRIO ABAJO					
24	EL CHILE	15	14	2	14	35
25	EL BOSQUE	11	11	0	0	0
26	CARPINTERO	4	4	0	0	0
27	BRISAS DE PICACHO	5	5	1	20	8
28	I.H.S.S. BARRIO ABAJO	S	S	S	0	0
	6- RED KENNEDY					
29	EL PEDREGAL	16	15	1	7	14
30	AEROPUERTO TONCONTIN	S	S	S	S	0
31	LA PEÑA (S.H.)	8	8	0	0	0
32	OSCAR A. FLORES	6	6	1	17	12
33	LA CAÑADA	11	11	2	18	40
34	LA JOYA	13	13	3	23	46
35	MONTERREY	14	14	2	14	38
	7- RED ALONSO SUAZO					
36	ALONSO SUAZO	59	56	3	5	61
37	LOS PINOS	18	18	2	11	15
38	ALDEA VILLA VIEJA	8	8	2	25	20
39	VILLA NUEVA	16	16	5	31	40
40	NUEVA SUYAPA	11	11	2	18	51
	8- RED ZAMBRANO					
41	ZAMBRANO	9	9	1	11	11
42	TAMARA	9	9	2	22	70
43	SAN MIGUEL ARCANGEL	6	6	0	0	0
44	CIUDAD ESPAÑA	10	10	1	10	13
45	VILLA EL PORVENIR	S	S	S	0	0
46	UAPS RIO FRIO	8	8	2	25	27
	TOTAL	**545**	**535**	**61**	**11**	**1297**

Programación Mesa Municipal Intersectorial

COLONIAS/BARRIOS	VIVIENDAS ATENDER	ACTIVIDAD	RESPONSABLES	FECHA	PUNTO DE REUNION
CIS Alonso Suazo Col. Kennedy sec. 95,97 y 98	1800	Fumigacion/aplicación BTI	COPECO	16 al 19 marzo	DPI
CIS Villanueva Col. Villa Nueva Sector 6	562	Fumigacion/aplicación BTI	RSM	16 al 20 marzo	Cis Villa Nueva
CIS Nueva Suyapa Col. 17 de septiembre	383	Fumigacion/aplicación BTI	AMDC	16 y 17 marzo	CIS Nueva Suyapa
CIS Nueva Suyapa Col. Nueva Suyapa Sector la Bandera	200	Fumigacion/aplicación BTI	AMDC	18.marzo	CIS Nueva Suyapa
CIS Nueva Suyapa Col. Nueva suyapa Sector Altos de AGAFAM	200	Fumigacion/aplicación BTI	AMDC	19.marzo	CIS Nueva Suyapa
CIS Nueva Suyapa Col. Nueva suyapa Sector Universidad	450	Fumigacion/aplicación BTI	AMDC	20.marzo	CIS Nueva Suyapa
CIS Nueva Esperanza		Operativo de limpieza	GAM	18.marzo	CIS Nueva Esperanza
CIS Nueva Suyapa		Operativo de limpieza	GAM	19 y 20 marzo	Cis Nueva Suyapa